ALMA MATER STUDIORUM
UNIVERSITÀ DI BOLOGNA

Dipartimento di Informatica - Scienza e Ingegneria - DISI

Corso di Laurea in Ingegneria e Scienze Informatiche

IMPLEMENTAZIONE CUDA DI UN ALGORITMO DI PROIEZIONE TOMOGRAFICA

Tesi di Laurea in Ingegneria e Scienze Informatiche

Relatore:
Prof. Moreno Marzolla

Correlatore:
Prof. Elena Loli Piccolomini

Presentata da:
Enrico Marchionni

Sessione marzo 2025

Anno Accademico 2024/2025

Sommario

La Tomografia Computerizzata (TC) è una tecnica diagnostica che sfrutta le radiazioni ionizzanti (o raggi X) per ottenere un'immagine tridimensionale di un'entità analizzata. Questa tecnica si basa sulla raccolta, da parte di un rilevatore, di una matrice di dati 2D. Tale matrice è costruita a partire da considerazioni fatte sull'attenuazione dei raggi X che, diretti da una sorgente verso il rilevatore, passano attraverso l'oggetto di studio, vagliandolo. Facendo ruotare la sorgente e il rilevatore, lungo una traiettoria nota, molte matrici di dati vengono in genere raccolte. Queste matrici 2D vengono poi trasferite in un calcolatore che ha il compito di ricostruire l'entità scansionata in 3D. Questo consente di esaminare l'oggetto ricostruito, osservandone alcune caratteristiche della sua struttura interna non note a priori, senza doverlo a tal scopo necessariamente disassemblare.

Nonostante sfruttata principalmente in ambito medico, la teoria su cui si basa la TC, in realtà, non fu ideata per scopi medici. Infatti tale tecnica trova applicazione in numerosi altri ambiti oltre alla medicina, tra cui vari settori industriali, la paleontologia, l'archeologia e numerosi altri campi.

Il principio su cui si basa ha origine grazie al matematico austriaco Johann Radon, che nel 1917 dimostrò la possibilità di ricostruire un oggetto tridimensionale mediante un numero infinito di proiezioni bidimensionali dell'oggetto stesso. Dal punto di vista matematico, questo rappresenta un problema inverso, cioè si determinano le cause (immagine 3D) a partire dagli effetti osservati (proiezioni 2D).

In questa analisi viene invece affrontato il problema diretto: partendo dal corpo studiato si devono perciò determinare le proiezioni che una TC potrebbe generare. Gli obiettivi di questo lavoro sono:

- Implementare una versione CUDA di un certo algoritmo di proiezione proposto da Siddon [Sid85] partendo da una sua implementazione parallela in C che sfrutta OpenMP [Col25].
- Analizzare le prestazioni della versione CUDA per GPU e confrontarle con la versione parallela per CPU già nota.

Indice

1 Introduzione **1**

1.1 Il modello matematico 1

1.1.1 La legge di Lambert-Beer 1

1.1.2 La trasformata di Radon 2

1.1.3 Il caso discreto 2

1.2 Algoritmo risolutivo 3

1.2.1 La matrice M 4

1.2.2 Il vettore f 4

1.3 Considerazioni geometriche 5

1.3.1 Posizionamento sorgente, oggetto e rilevatore nello spazio 5

1.3.2 Le sorgenti 6

1.3.3 L'oggetto 6

1.3.4 I rilevatori 7

1.3.5 I raggi 8

A Conclusioni **11**

Capitolo 1

Introduzione

Una proiezione è una matrice i cui valori rappresentano l'attenuazione dei raggi X che attraversano il corpo oggetto di studio. Considerando un'immagine generata a partire dalla matrice proiezione, i colori rappresentano graficamente i vari livelli di attenuazione: un raggio che attraversa una regione più densa del corpo subisce una maggiore attenuazione rispetto ad un raggio che attraversa una regione meno densa.

Durante una scansione tomografica sono acquisite numerose immagini attorno all'oggetto di studio. Nel caso più semplice, che noi analizzeremo, si possono considerare le diverse angolazioni di una traiettoria circolare. Intuitivamente più sono le proiezioni acquisite, più la ricostruzione dell'oggetto sarà efficace. D'altra parte, specialmente in ambito medico, ridurre l'esposizione alle radiazioni è di beneficio per l'individuo scansionato. Questo implica che il numero di proiezioni generate è esso stesso molto variabile in base all'applicazione.

Nelle sezioni successive verrà illustrato il modello matematico che costituisce la base della computazione, mettendolo in relazione diretta con le sue applicazioni nell'algoritmo risolutivo. Infine, sarà esaminato il problema dal punto di vista geometrico.

1.1 Il modello matematico

Di seguito verranno discusse le nozioni matematiche fondamentali per comprendere, dal punto di vista algebrico, il calcolo alla base della creazione delle proiezioni, vedi [MP21].

1.1.1 La legge di Lambert-Beer

Dal punto di vista fisico, i dati di proiezione riflettono l'assorbimento dei fotoni che costituiscono i raggi X. Il modello fisico che descrive l'assorbimento dei fotoni in termini di coefficienti di attenuazione è descritto dalla legge di Lambert-Beer.

Il meccanismo fisico che porta all'attenuazione dell'intensità dei raggi è solitamente descritto da un singolo coefficiente di attenuazione $\mu = \mu(w) \geq 0$ che dipende dalla posizione lungo il percorso del raggio, indicata da w. Questi coefficienti determinano i vari $m(w)$, cioè le intensità del raggio nella posizione indicata da w.

La **legge di Lambert-Beer** per il calcolo della proiezione del coefficiente di attenuazione lungo un segmento di lunghezza W è:

$$P_W \mu = -\ln\left(\frac{m}{m_0}\right) = \int_0^W \mu(w)\, dw \tag{1.1}$$

Dove:

- m è l'intensità finale del raggio, dopo aver attraversato il materiale.
- m_0 è l'intensità iniziale del raggio.
- $\mu(w)$ è una funzione continua che descrive il coefficiente di attenuazione alla posizione w lungo il raggio.
- W è la lunghezza totale del percorso attraverso il materiale.

1.1.2 La trasformata di Radon

La **trasformata di Radon**, in un modello continuo, è data dall'insieme delle proiezioni acquisite lungo l'intera traiettoria circolare. La rappresentazione grafica di tutti i dati misurati nel caso bidimensionale è chiamata *sinogramma*.

1.1.3 Il caso discreto

Nel caso discreto il corpo è diviso in volumi più piccoli, detti **voxel**, che sono elementi di dimensione molto piccola in cui il corpo è approssimato. Per ciascun voxel il coefficiente di attenuazione è un valore approssimato costante.

L'Equazione 1.1 nel caso discreto, per calcolare una singola proiezione, diventa:

$$g_i = \sum_{j=0}^{N} M_{i,j} f_j \quad \forall i \in 1, \ldots, n_p \tag{1.2}$$

Dove:

- i è l'i-esimo raggio, degli n_p considerati per quella proiezione.
- j è il j-esimo voxel, degli N totali che approssimano il corpo.
- g_i è l'attenuazione subita dall'i-esimo raggio.
- $M_{i,j}$ è una matrice di $n_p \times N$ elementi che per ogni raggio i definisce la lunghezza della porzione sottesa al volume di ciascun voxel j.
- f_j è il valore del coefficiente di attenuazione assunto nel volume interno al j-esimo voxel.

Matematicamente quindi, per il calcolo delle proiezioni, viene considerata un'approssimazione dell'oggetto analizzato, vedi Figura 1.1.

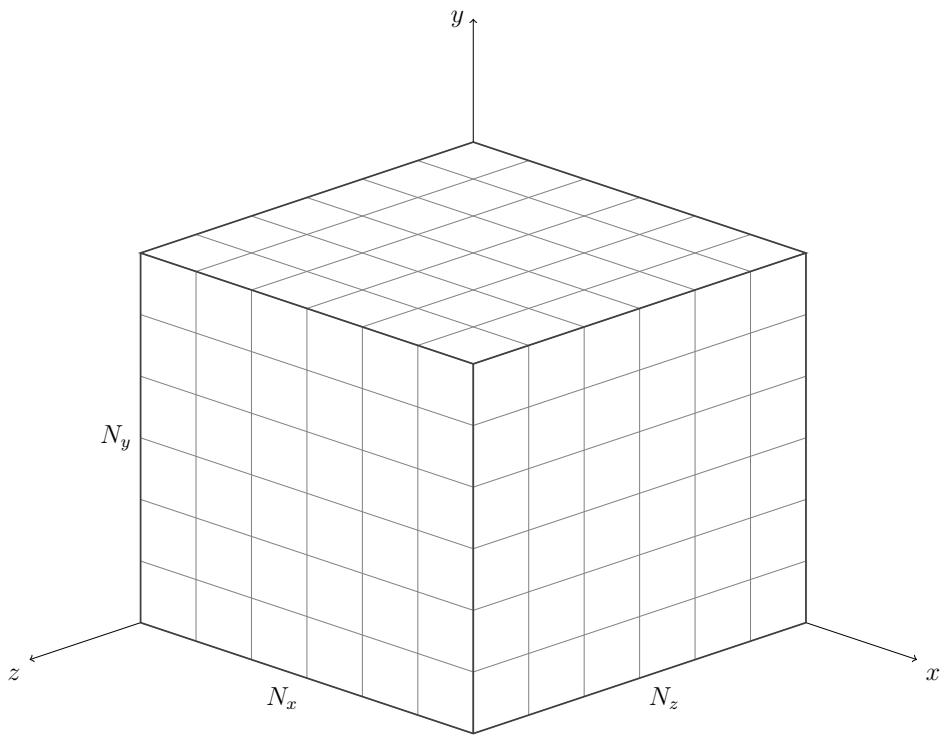

Figura 1.1: Esempio di oggetto cubico suddiviso in $N = N_x \times N_y \times N_z$ voxel cubici. Nel caso generale i voxel sono dei parallelepipedi retti, nel caso più semplice possono essere dei cubi con una dimensione $d = d_x = d_y = d_z$ fissata in base alle necessità.

Nel caso discreto della trasformata di Radon il numero di proiezioni dipende dal numero di posizioni considerate in cui si effettuano le scansioni, tale numero verrà di seguito indicato con N_θ. Ad ogni posizione la sorgente ed il rilevatore sono posti in modo da poter analizzare lo stesso oggetto da più angolazioni diverse.

1.2 Algoritmo risolutivo

Considerando quanto già visto nel modello matematico, nel nostro caso l'algoritmo di Siddon si occupa di calcolare la matrice M, mentre il vettore f deve essere già noto in partenza. Questa dati devono essere determinati per poter procedere con la computazione.

L'algoritmo svolge una computazione equivalente a quella descritta nell'Equazione 1.2:

$$d = \sum_i \sum_j \sum_k l(i,j,k)\rho(i,j,k)$$

dove i parametri i, j e k individuano un singolo voxel nello spazio tridimensionale. In particolare, considerando una specifica configurazione di (i,j,k), l rappresenta la lunghezza sottesa in quel voxel (equivalente di M) mentre ρ rappresenta la densità del voxel (equivalente di f).

1.2.1 La matrice M

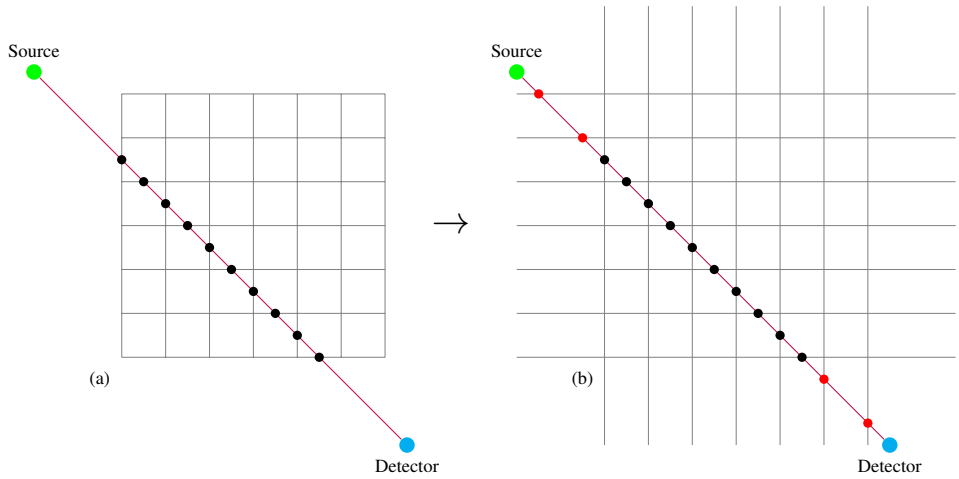

Figura 1.2: Pixel (voxel nel caso 2D) considerati come rette parallele che rappresentano la struttura dell'oggetto considerato. Come si può notare alcune intersezioni tra il raggio e i piani non sono valide perché fuori dalla griglia, vedi i puntini rossi della figura *b*.

I punti chiave dell'algoritmo, nella determinazione della matrice M, possono essere così riassunti:

- L'algoritmo considera, invece dei singoli voxel indipendenti, tre insiemi di piani ortogonali ed equidistanti tra loro che vanno a costruire la griglia di discretizzazione del corpo nello spazio, vedi Figura 1.2.
- Si calcolano i punti di intersezione tra le rette, i raggi, e i piani che definiscono i voxel.
- Si calcola la lunghezza dei segmenti sottesi ai voxel, come la differenza tra punti di intersezione consecutivi, determinando così la matrice M.

1.2.2 Il vettore f

Il vettore f rappresenta il coefficiente di attenuazione assunto nella regione interna al volume sotteso da ciascun voxel. Presenta dunque un numero di elementi pari al numero di voxel in cui è suddiviso l'oggetto.

Le tre diverse configurazioni, fornite da [Col25], sono state qui riutilizzate:

- Un **cubo**: stabilita la lunghezza del lato del cubo che si intende rappresentare, gli elementi all'interno della regione cubica sono posti ad 1, altrimenti a 0.
- Una **semi-sfera**: stabilita la lunghezza del raggio della semisfera che si intende rappresentare, gli elementi all'interno della regione semisferica sono posti ad 1, altrimenti a 0.
- Un **cubo con cavità sferica**: stabilita la lunghezza del lato del cubo che si intende rappresentare, gli elementi all'interno della regione cubica, ad eccezione da quelli la cui distanza da un punto stabilito all'interno dell'oggetto sia inferiore ad un raggio stabilito, sono posti ad 1, altrimenti a 0.

1.3 Considerazioni geometriche

Questa sezione approfondisce le considerazioni geometriche necessarie per poter procedere con l'implementazione dell'algoritmo di Siddon.

1.3.1 Posizionamento sorgente, oggetto e rilevatore nello spazio

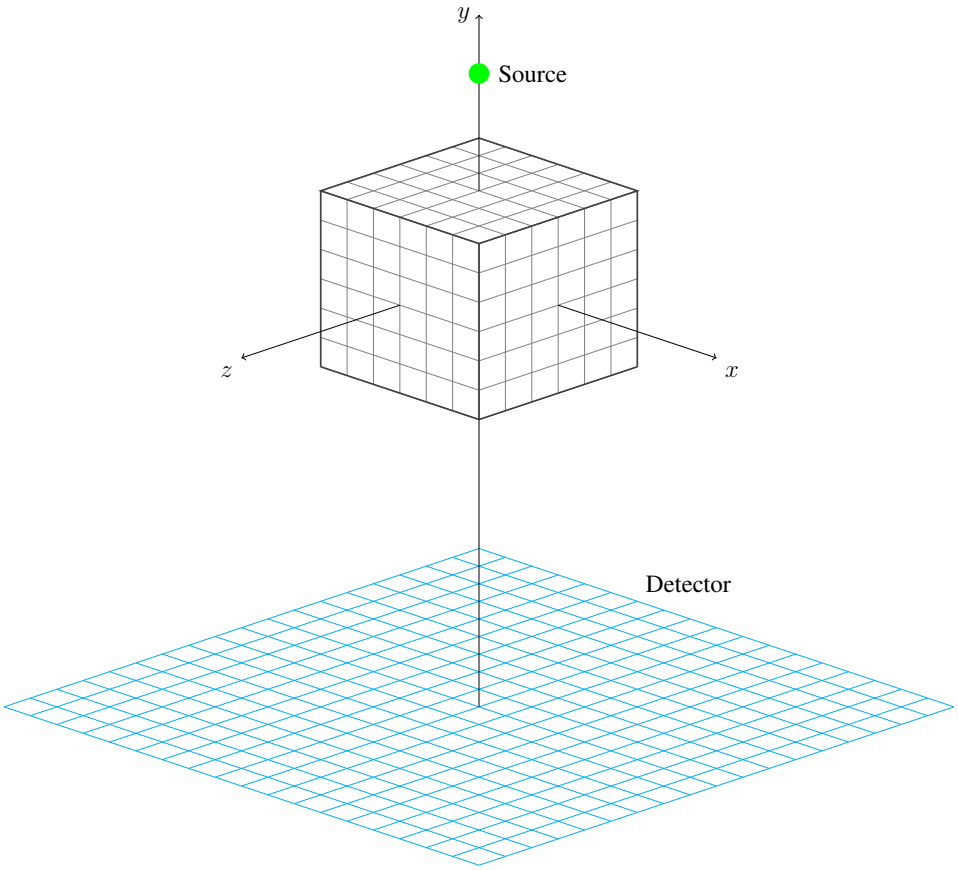

Figura 1.3: Esempio che rappresenta l'oggetto cubico già visto in Figura 1.1 nel sistema di riferimento cartesiano considerato nelle discussioni seguenti.

In Figura 1.3 sono rappresentati un oggetto di forma cubica, la sorgente ed il rilevatore, tutti posti in uno specifico sistema cartesiano, in cui il centro dell'oggetto corrisponde con l'origine degli assi.

Nel nostro caso la posizione del punto sorgente, da cui partono i raggi, e dei pixel del rilevatore, al centro di cui questi vengono a dirigersi, ruotano in un'orbita circolare in modo da scansionare il corpo da più posizioni.

Quando la sorgente ruota in un senso nelle specifiche posizioni dell'orbita, il rilevatore ruota coerentemente nel senso opposto.

1.3.2 Le sorgenti

La sorgente è approssimata ad un punto, che indica la posizione a partire dalla quale sono diretti i raggi. Le posizioni considerate sono più di una e sono distribuite, nell'implementazione trattata, lungo una traiettoria circolare (o una sezione di essa) intorno all'oggetto. Rimane da stabilirne ciascuna coordinata nello spazio.

Conoscendo l'estensione angolare θ della sezione della traiettoria considerata e la distanza angolare α tra ciascuna posizione, si è scelto l'uso delle coordinate polari, dove una posizione è individuata dalla distanza dall'origine e dalla distanza angolare dall'asse polare. In accordo con la Figura 1.3, viene considerato un sistema di coordinate polari il cui polo coincide con il centro dell'oggetto di studio, mentre si adotta l'asse y come asse polare. La distanza angolare è positiva in senso orario nel piano xy.

La posizione della sorgente può essere individuata nel seguente modo:

$$(d_s, -\theta/2 + \alpha i) \quad \text{per } i = 0, \ldots, N_\theta - 1 \tag{1.3}$$

dove:

- i è un indice che identifica una posizione della sorgente.
- d_s è la distanza sorgente-origine.
- N_θ è il numero di posizioni dato dal rapporto $N_\theta = \lfloor \theta/\alpha \rfloor + 1$.

Le coordinate cartesiane si ottengono a partire dalle coordinate polari nel seguente modo:

$$\begin{cases} X_i = \cos(\frac{\pi}{2} - (-\frac{\theta}{2} + \alpha i))d_s = \sin(-\frac{\theta}{2} + \alpha i)d_s \\ Y_i = \sin(\frac{\pi}{2} - (-\frac{\theta}{2} + \alpha i))d_s = \cos(-\frac{\theta}{2} + \alpha i)d_s \\ Z_i = 0 \end{cases} \quad \text{per } i = 0, \ldots, N_\theta - 1 \tag{1.4}$$

dove sono state applicate le formule degli archi associati per seno e coseno per passare dal sistema con misurazione in senso orario a partire dal semiasse positivo delle y al sistema tradizionale con misurazione in senso antiorario a partire dal semiasse positivo delle x. Inoltre, Z_i è posta a 0 in quanto, per costruzione, la traiettoria giace sul piano xy.

1.3.3 L'oggetto

Un oggetto è approssimato da un certo numero di voxel, cioè parallelepipedi retti con dimensioni uniformi l'uno con l'altro. Le griglie che questi creano, dall'algoritmo di Siddon, sono rappresentate da un certo numero di piani paralleli tra loro.

L'equazione cartesiana di un piano nello spazio è un'equazione di primo grado in tre incognite:

$$ax + by + cz + d = 0 \quad \text{con } a, b, c, d \in \Re$$

Avendo in mente la Figura 1.3, i piani coinvolti, oltre che ad essere paralleli tra di loro, sono paralleli anche agli assi cartesiani. Dunque, le loro equazioni sono nella forma:

$$\begin{aligned} ax + d = 0 &\quad \text{se parallelo al piano } yz \\ by + d = 0 &\quad \text{se parallelo al piano } xz \\ cz + d = 0 &\quad \text{se parallelo al piano } xy \end{aligned}$$

Dato che le distanze tra i piani paralleli sono regolari, avendo l'equazione di un piano è possibile determinare l'equazione degli altri traslando più volte. L'equazione degli altri piani a partire dal primo si determina nel seguente modo:

$$\begin{aligned} X_{plane}(i) &= X_{plane}(1) + (i-1)d_x \quad \forall i \in 1, \dots, N_x \\ Y_{plane}(j) &= Y_{plane}(1) + (j-1)d_y \quad \forall j \in 1, \dots, N_y \\ Z_{plane}(k) &= Z_{plane}(1) + (k-1)d_z \quad \forall k \in 1, \dots, N_z \end{aligned}$$

dove N_x, N_y e N_z sono il numero di voxel lungo gli assi x, y e z, mentre d_x, d_y e d_z sono a loro volta le dimensioni di un singolo voxel lungo i tre assi cartesiani.

1.3.4 I rilevatori

Nel caso tridimensionale, il rilevatore può essere visto come una matrice di unità di misura, ossia i pixel, posizionata a una distanza d_r dal centro del corpo in esame.

L'approccio usato per relazionare i raggi con il rilevatore è detto *ray-driven*. Per ciascun unità del rilevatore si considera l'esistenza di un unico raggio passante, diretto dalla sorgente al centro del pixel stesso. Secondo questo approccio, il numero n_p di raggi usati per il calcolo della proiezione coincide con il numero di pixel del rilevatore.

Il rilevatore è sempre ortogonale all'asse che congiunge la sorgente ed il centro del corpo.

Le coordinate cartesiane del centro di un'unità del rilevatore, al variare dell'angolo considerato, sono (X', Y', Z'), derivate dalla posizione (X, Y, Z), ricoperta nel caso in cui il rilevatore sia ortogonale all'asse y.

Considerando il semiasse negativo di y come asse polare, anche questa volta con angolo positivo in senso orario, le coordinate polari del punto sono:

$$(d_r, \delta)$$

dove δ è l'angolo che identifica l'unità del rilevatore.

Le coordinate a seguito della traslazione saranno:

$$(d_r, \delta - \lambda)$$

dove $-\lambda$ è l'angolo di traslazione.

Le coordinate di tale posizione traslata sono date da:

$$\begin{cases} X' = \cos(\frac{3\pi}{2} - (\delta - \lambda))d_r = -\sin(\delta - \lambda)d_r \\ Y' = \sin(\frac{3\pi}{2} - (\delta - \lambda))d_r = -\cos(\delta - \lambda)d_r \end{cases} \tag{1.5}$$

dove, in modo analogo all'Equazione 1.4, sono state applicate le formule degli archi associati per seno e coseno per passare dal sistema con misurazione in senso orario a partire dal semi asse negativo delle y al sistema tradizionale con misurazione in senso antiorario a partire dal semi asse positivo delle x. In questo caso Z è costante, $Z' = Z$, in quanto, per costruzione, la traiettoria trasla sul piano xy, senza influire sulla coordinata nell'asse z, quindi verrà omessa nella discussione seguente.

A partire dall'Equazione 1.5, applicando le formule di addizione degli archi per seno e coseno si ottiene:

$$\begin{cases} X' = -(\sin(\delta)\cos(-\lambda)d_r + \cos(\delta)\sin(-\lambda)d_r) \\ Y' = -(\cos(\delta)\cos(-\lambda)d_r - \sin(\delta)\sin(-\lambda)d_r) \end{cases}$$

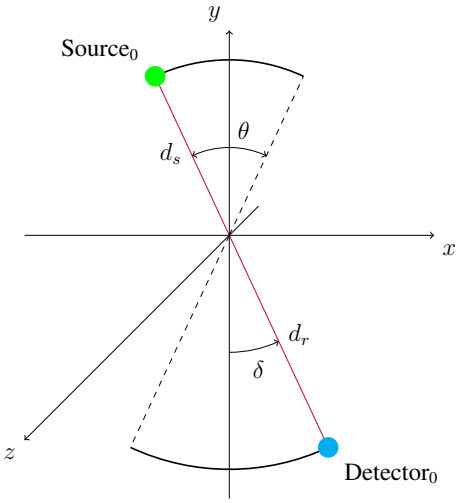

Figura 1.4: Vista goniometrica di un raggio diretto dalla prima sorgente verso il centro del pixel centrale nella matrice che rappresenta il rilevatore.

Osservando Figura 1.4, dalle formule trigonometriche per i triangoli rettangoli:

$$d_r = -\frac{X}{\sin(\delta)} = -\frac{Y}{\cos(\delta)}$$

sostituendo d_r e sfruttando le formule degli archi associati per seno e coseno si ottiene:

$$\begin{cases} X' = \cos(-\lambda)X + \sin(-\lambda)Y \\ Y' = \cos(-\lambda)Y - \sin(-\lambda)X \end{cases}$$

Analogamente a quanto avviene con la sorgente, la posizione di una unità del rilevatore varia, ad intervalli regolari, di un angolo α su di una sezione di ampiezza regolare pari a θ. Quindi, ricordando l'Equazione 1.3, si considera $-\lambda = -\theta/2 + \alpha i$. Le posizioni di un'unità del rilevatore possono dunque essere ottenute, a partire dalla posizione precedente, con:

$$\begin{cases} X'_i = \cos(-\theta/2 + \alpha i)X + \sin(-\theta/2 + \alpha i)Y \\ Y'_i = \cos(-\theta/2 + \alpha i)Y - \sin(-\theta/2 + \alpha i)X \end{cases} \qquad \text{per } i \in 0, \ldots, N_\theta - 1$$

1.3.5 I raggi

Un raggio, approssimazione di radiazioni elettromagnetiche, è considerato come un segmento che, nell'implementazione usata, collega la sorgente con il centro di un pixel del rilevatore (approccio ray-driven).

Può essere rappresentato mediante l'equazione parametrica di una retta passante per due punti $Source = (X_1, Y_1, Z_1)$ e $Detector = (X_2, Y_2, Z_2)$:

$$X(a) = X_1 + a(X_2 - X_1)$$
$$Y(a) = Y_1 + a(Y_2 - Y_1)$$
$$Z(a) = Z_1 + a(Z_2 - Z_1)$$

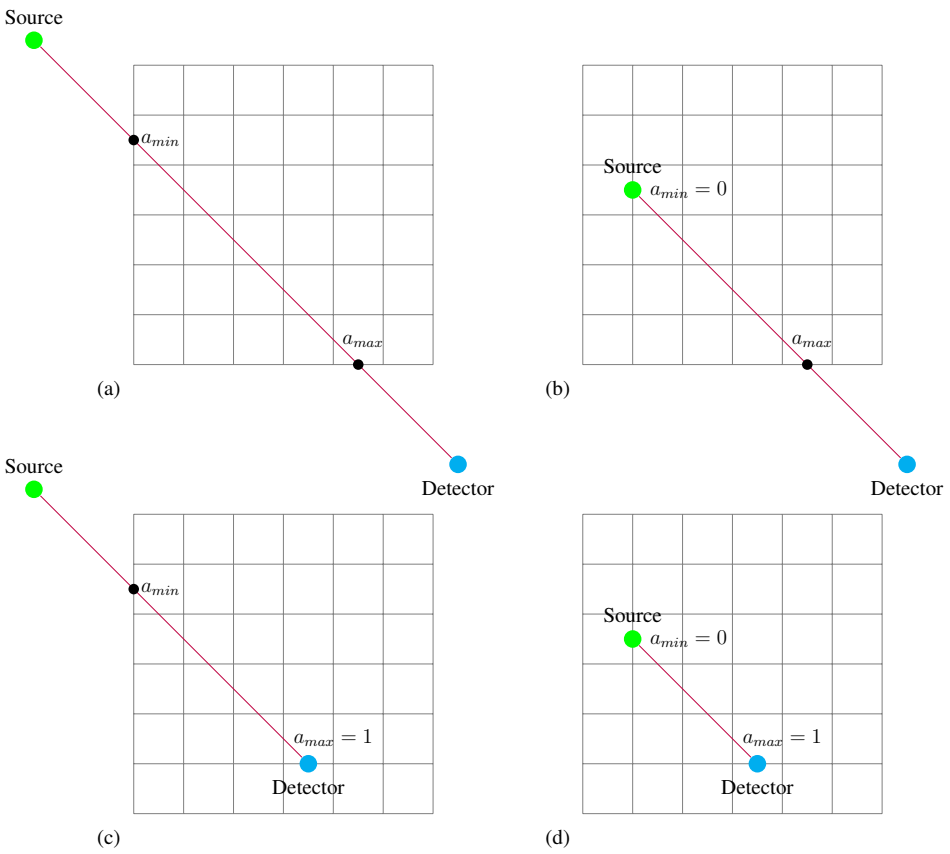

Figura 1.5: Le quantità a_{min} e a_{max} sono quelle che definiscono i range da considerare per ottenere solo le intersezioni con piani effettivamente all'interno della griglia di pixel (voxel nel caso 3D). Si può notare che a_{min} nelle figure *a* e *c* sarà maggiore di 0, così come a_{max} nelle figure *a* e *b* sarà minore di 1. Questo permette di non considerare le intersezioni in eccesso, esterne alla griglia di partenza, risolvendo il problema esposto nella Figura 1.2.

In questo modo:

- Per definire un raggio basta conoscere il punto "sorgente" ed il punto sul "rilevatore" dove avviene la misurazione.
- È possibile rappresentare un punto appartenente alla retta del raggio attraverso un unico parametro a, in particolare $a = 0$ coincide con il punto $Source$, $a = 1$ coincide con il punto $Detector$, per i valori di a compresi tra $[0, 1]$ si hanno punti interni al segmento, vedi Figura 1.5.

Il punto di intersezione di un raggio ed un piano lo si ottiene risolvendo in a il sistema lineare dato dall'equazione del piano e una componente della retta come di seguito:

$$\begin{cases} X = X_1 + a(X_2 - X_1) \\ X = X_{planes}(1) + (i-1)d_x \end{cases} \qquad \text{se } i \in 1, \ldots, N_x$$

$$\begin{cases} Y = Y_1 + a(Y_2 - Y_1) \\ Y = Y_{planes}(1) + (i-1)d_y \end{cases} \qquad \text{se } i \in 1, \ldots, N_y$$

$$\begin{cases} Z = Z_1 + a(Z_2 - Z_1) \\ Z = Z_{planes}(1) + (i-1)d_z \end{cases} \qquad \text{se } i \in 1, \ldots, N_z$$

dove sono stati indicati i sistemi utilizzati nel caso in cui il piano sia parallelo al piano yz (primo sistema), al piano xz (secondo sistema) o al piano xy (terzo sistema).

Appendice A

Conclusioni

...

Bibliografia

[Col25] Lorenzo Colletta. "Implementazione parallela di un algoritmo di proiezione tomografica". Tesi di laurea triennale. Ingegneria e Scienze Informatiche, Università di Bologna, Cesena, 2024/2025.

[MP21] Elena Morotti e Elena Loli Piccolomini. "Sparse Regularized CT Reconstruction: An Optimization Perspective". In: *Handbook of Mathematical Models and Algorithms in Computer Vision and Imaging: Mathematical Imaging and Vision*. A cura di Ke Chen et al. Cham: Springer International Publishing, 2021, pp. 1–34. ISBN: 978-3-030-03009-4. DOI: 10.1007/978-3-030-03009-4_123-1. URL: https://doi.org/10.1007/978-3-030-03009-4_123-1.

[Sid85] Robert L. Siddon. "Fast calculation of the exact radiological path for a three-dimensional CT array". In: *Medical Physics* 12.2 (1985), pp. 252–255. DOI: https://doi.org/10.1118/1.595715. eprint: https://aapm.onlinelibrary.wiley.com/doi/pdf/10.1118/1.595715. URL: https://aapm.onlinelibrary.wiley.com/doi/abs/10.1118/1.595715.